# 物　件　概　要　書

| | | | | | |
|---|---|---|---|---|---|
| 物件名 | 三鷹市井の頭五丁目底地、土地 | | | | |
| 所　在 | （住居表示）　東京都三鷹市井の頭五丁目5-21　他 | | | | |
| | （地　　番）　三鷹市井の頭五丁目904番9、904番38、904番1（持分5分の2）、904番24 | | | | |
| 駅 | 京王井の頭線『井の頭公園』駅　徒歩9分 | | | | |
| 土　地 | 地積（公簿） | 1,207.91㎡ | 365.39坪 | 地　目 | 宅地 |
| | 地積（実測） | 1,206.54㎡ | 364.97坪 | 権　利 | 所有権（一部底地権） |
| | ※上記地積はセットバック面積を含んでおります。<br>※別途私道112.83㎡（持分5分の2）（地番904番1）があります。 | | | | |
| 法規制 | 用途地域 | 第1種低層住居専用地域 | | 防火規制 | 準防火地域 |
| | 建ぺい率 | 40% | | 容積率 | 80% |
| | その他 | 絶対高さ：10m、最低敷地面積：100㎡、第1種高度地区、日影規制：3h-2h（1.5m） | | | |
| 接　道 | 北西側構造（1項1号）　接道約18.89m<br>北東側私道（42条2項）　接道約25.95m、幅員約1.47～2.74m | | | | |
| 価　格 | | | | | |
| 路線価 | 165万円/坪（50万円/㎡） | | | 底地権割合 | 40% |
| 賃貸借契約（1区画） | 契約期間 | 2011年4月1日から2031年3月31日 | | 月額地代 | 28,734円 |
| | 建　物 | 木造瓦葺2階建 | | | |

住宅地図

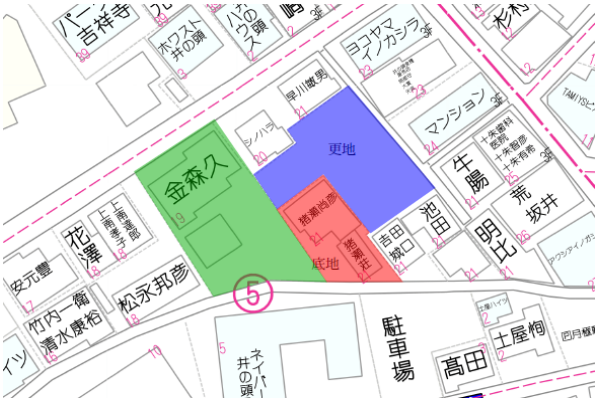


| | |
|---|---|
| 備考 | ※対象地のうち、地番904番9は底地権、904番38は所有権（現況更地）、904番24（古家有）となります。 |

※上記法制限等は都市計画法により定められた数値であり、道路幅員・各斜線・高度制限・容積移転等を考慮した数値ではありません。また、地方公共団体等により、別途制限を受ける場合があります。
※上記内容は変更される場合があります。現況と異なる場合は、現況を優先するものとします。
※詳細は適宜お問い合わせ願います。


エリアリンク株式会社
Arealink

取引態様：媒介
東京都知事（5）第79635号
エリアリンク 株式会社
〒101-0021　東京都千代田区外神田4-14-1
TEL 03-3526-8572　FAX 03-3526-8579

東京都三鷹市井の頭5丁目5付近

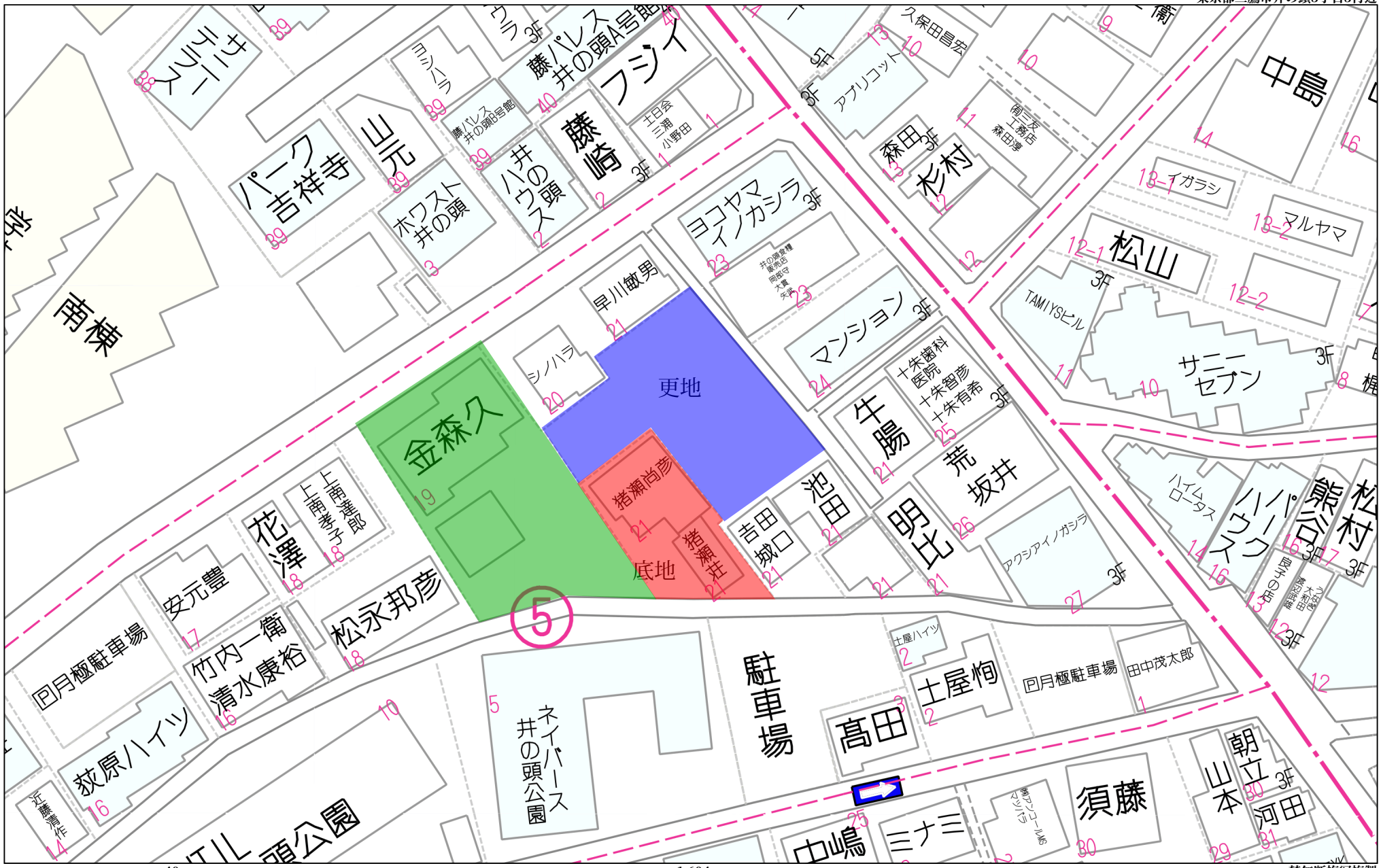
更地
底地
金森久
猪瀬尚彦
猪瀬共
駐車場
ネイバース井の頭公園
回月極駐車場
田中茂太郎
土屋恂
髙田
須藤
朝立山本
河田
中嶋
三ナ三
荻原ハイツ
竹内一衛
清水康裕
松永邦彦
安元豊
花澤
上西雅郎
上西孝子
シノハラ
早川敏男
ヨコヤマ
イノカシラ
マンション
牛腸
十朱歯科医院
十朱智彦
十朱有希
荒
坂井
池田
吉田
城口
明比
アクシアイノカシラ
ハイムロータス
ノーブル
イケブクロ
藤崎
ハイツ井の頭
ハイツ井の頭
ハウス井の頭
ホワスト井の頭
山元
パーク吉祥寺
藤パレス井の頭A号館
藤パレス井の頭B号館
フジイ
ヨシハラ
ウラ
アプリコット
久保田昌宏
森田
杉村
尚三及上務店
森田淳
中島
イガラシ
マルヤマ
松山
TAMIYSビル
サニーセブン
ハイツ
ハイツ
ハイツ

表示年月日：２０２３／０２／２４

イ 892-10　ハ 892-15　ホ 892-16　ト 902-13　リ 904-29　ル 901-5
ロ 892-13　ニ 892-15　ヘ 892-17　チ 903-12　ヌ 900-4

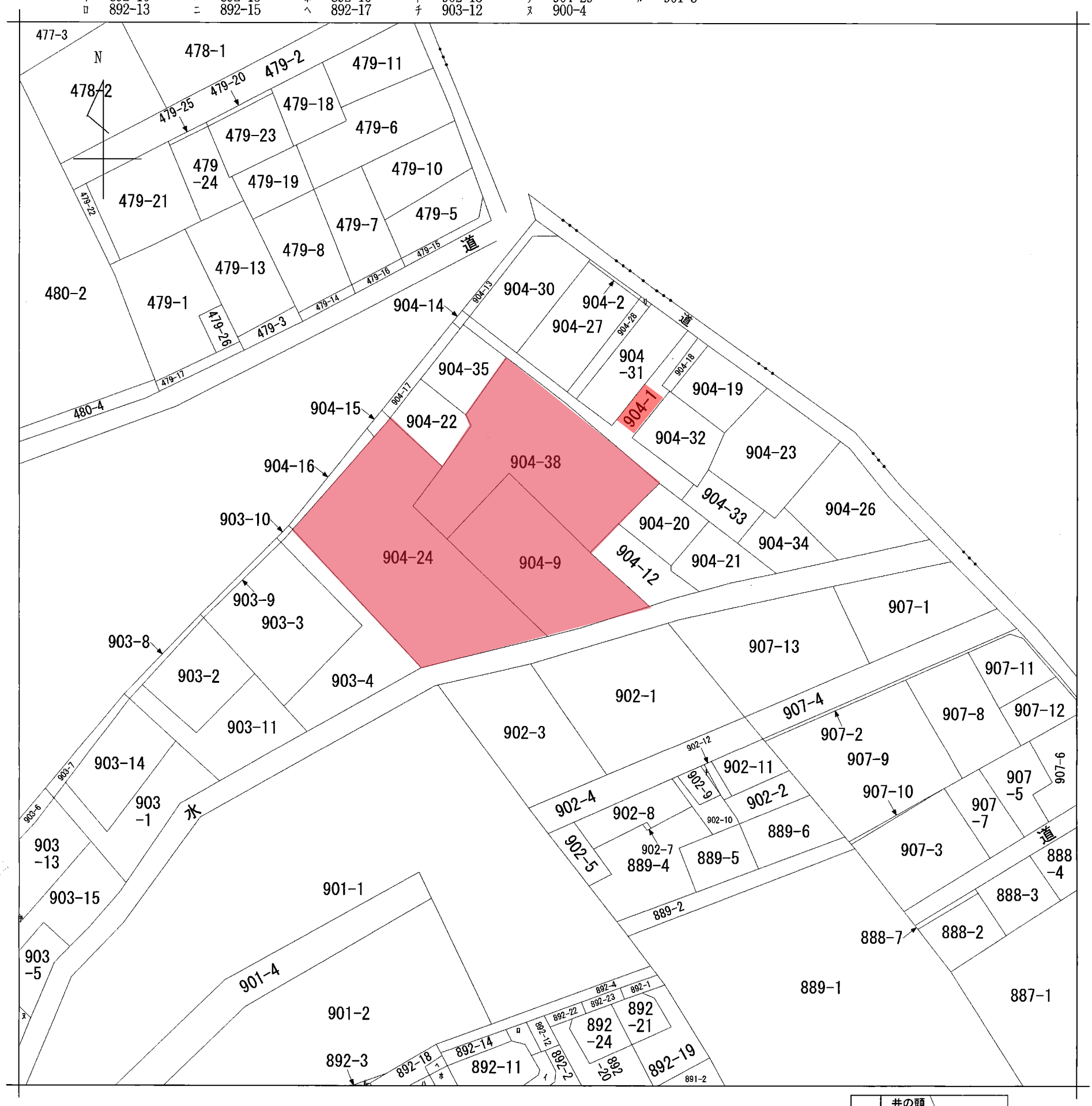


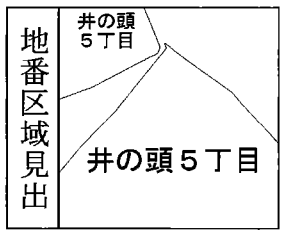


| | | | | | | | | | |
|---|---|---|---|---|---|---|---|---|---|
| 請求部分 | 所　在 | 三鷹市井の頭五丁目 | | | | | 地　番 | 904番9 | |
| 出力縮尺 | 1/600 | 精度区分 | | 座標系番号又は記号 | | 分類 | 地図に準ずる図面 | 種類 | 旧土地台帳附属地図 |
| 作成年月日 | | | | 備付年月日（原図） | | | 補記事項 | | |

| 地　　番 | 904-9・904-38 |
|---|---|
| 土地の所在 | 三鷹市井の頭五丁目 |

# 地 積 測 量 図

1/2

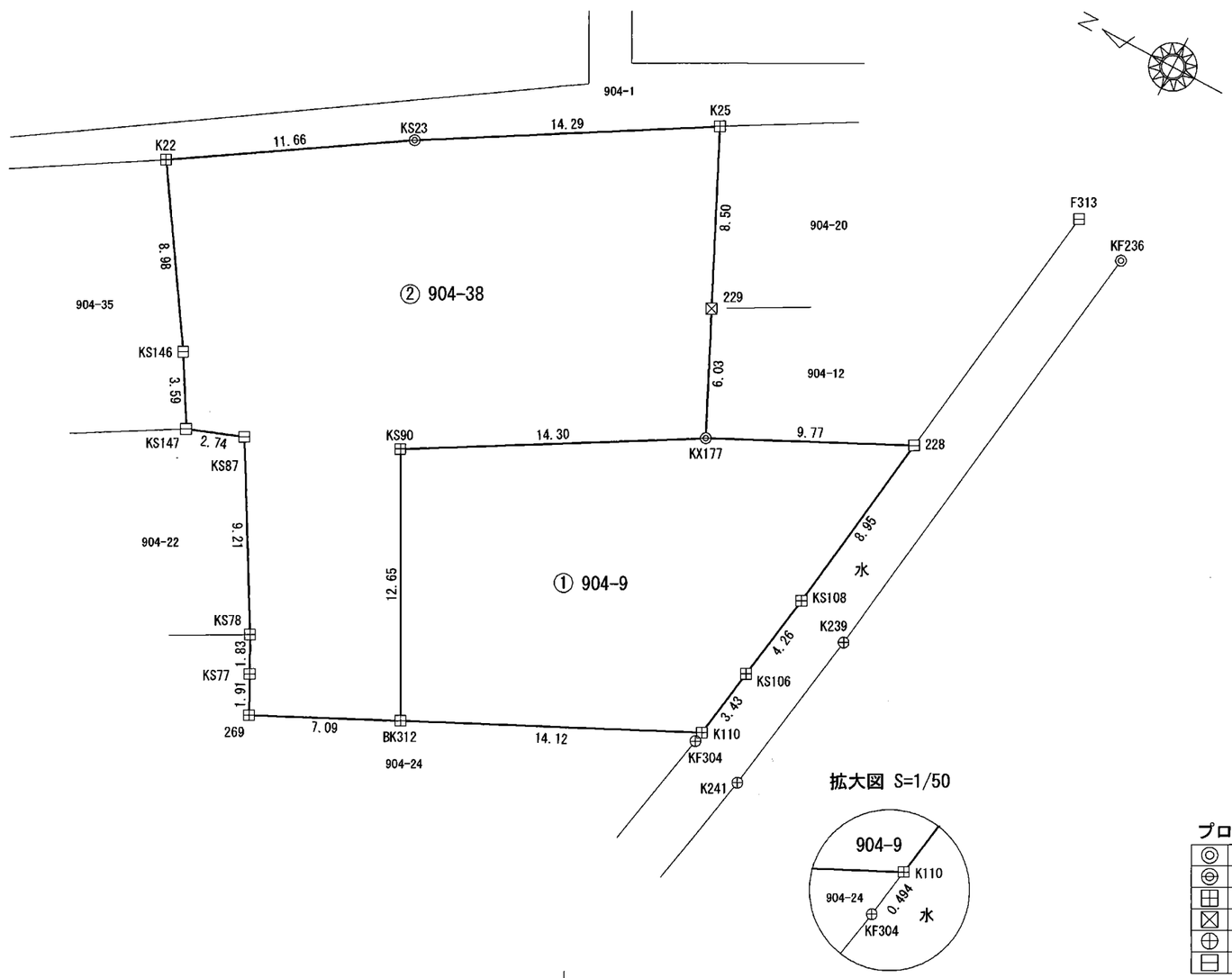


プロットマーク凡例

| | |
|---|---|
| ◎ | 市コンクリート杭 |
| ⊖ | 御影石 |
| ⊞ | 民コンクリート杭 |
| ⊠ | 民金属標 |
| ⊕ | 民鋲 |
| ⊟ | 民金属標（計算点） |

| 作 成 者 | 横浜市保土ヶ谷区上星川一丁目４－１６－２ぷらす上星川１Ｆ<br>土地家屋調査士法人アドフィールド登記測量事務所<br>社員土地家屋調査士 加 野 亮 一　（令和 5 年 2 月 9 日作成） | 申 請 人 | 株式会社クランピーリアルエステート<br>代表取締役 大江　剛 | 縮尺 | 1/250 |
|---|---|---|---|---|---|

| 地　　番 | 904-9・904-38 |
|---|---|
| 土地の所在 | 三鷹市井の頭五丁目 |

# 地 積 測 量 図

(2/2)

## 求 積 表

| 地　番 | ① 904-9 | | | |
|---|---|---|---|---|
| NO | Xn | Yn | Yn+1-Yn-1 | Xn・(Yn+1-Yn-1) |
| KS90 | 92.685 | 87.270 | -18.329 | -1698.823365 |
| BK312 | 86.753 | 76.088 | -5.049 | -438.015897 |
| K110 | 74.025 | 82.221 | 9.528 | 705.310200 |
| KS106 | 73.474 | 85.616 | 7.603 | 558.622822 |
| KS108 | 72.779 | 89.824 | 13.071 | 951.294309 |
| 228 | 71.505 | 98.687 | 4.593 | 328.422465 |
| KX177 | 80.299 | 94.417 | -11.417 | -916.773683 |
| | | | 合　計 | -509.963149 |
| | | | 合　計　面　積 | 254.9815745 |
| | | | 地　積 | 254.98　㎡ |

| 地　番 | ② 904-38 | | | |
|---|---|---|---|---|
| NO | Xn | Yn | Yn+1-Yn-1 | Xn・(Yn+1-Yn-1) |
| K22 | 108.684 | 94.053 | -13.782 | -1497.882888 |
| KS146 | 103.789 | 86.516 | -10.643 | -1104.626327 |
| KS147 | 101.986 | 83.410 | -2.161 | -220.391746 |
| KS87 | 99.408 | 84.355 | -7.070 | -702.814560 |
| KS78 | 94.869 | 76.340 | -9.638 | -914.347422 |
| KS77 | 94.018 | 74.717 | -3.334 | -313.456012 |
| 269 | 93.148 | 73.006 | 1.371 | 127.705908 |
| BK312 | 86.753 | 76.088 | 14.264 | 1237.444792 |
| KS90 | 92.685 | 87.270 | 18.329 | 1698.823365 |
| KX177 | 80.299 | 94.417 | 12.602 | 1011.927998 |
| 229 | 82.885 | 99.872 | 13.142 | 1089.274670 |
| K25 | 86.528 | 107.559 | 0.426 | 36.860928 |
| KS23 | 98.836 | 100.298 | -13.506 | -1334.879016 |
| | | | 合　計 | -886.360310 |
| | | | 合　計　面　積 | 443.1801550 |
| | | | 地　積 | 443.18　㎡ |

| 総合計面積 | 698.1617295　㎡ |
|---|---|

| 測量年月日 | 令和5年 2月 3日 |
|---|---|
| 座標系 | 任意座標 |

### 引照点座標一覧表

| 点　名 | X座標 | Y座標 | 備　考 |
|---|---|---|---|
| F313 | 69.648 | 111.602 | 水路境界標 |
| K239 | 70.135 | 89.036 | 水路境界標 |
| K241 | 71.458 | 80.946 | 水路境界標 |
| KF236 | 67.011 | 110.818 | 水路境界標 |
| KF304 | 74.105 | 81.733 | 水路境界標 |

（ 任 意 座 標 ）

| 作 成 者 | 横浜市保土ヶ谷区上星川一丁目４－１６－２ぷらす上星川１Ｆ<br>土地家屋調査士法人アドフィールド登記測量事務所<br>社員土地家屋調査士 加 野 亮 一　（令和 5 年 2 月 9 日作成） |
|---|---|

| 申 請 人 | 株式会社クランピーリアルエステート<br>代表取締役 大江　剛 | 縮尺 | 1／250 |
|---|---|---|---|

# 土地確定測量図

土地の所在地

三鷹市井の頭五丁目904番24

公図写　縮尺1/600

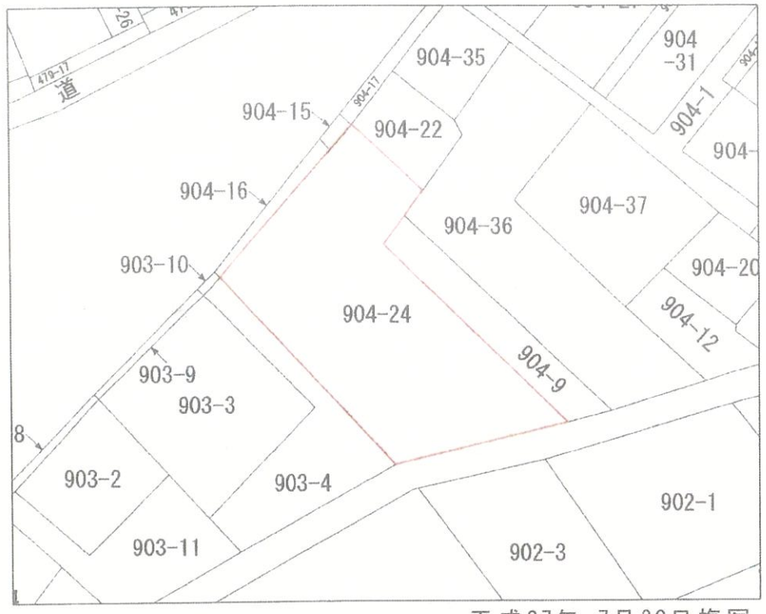


平成27年　7月30日複写

座標求積表

| 地番 | ① 904-24 | | |
|---|---|---|---|
| 測点 | Xn | Yn | (Xn+1−Xn−1) Yn |
| K9 | 460.412 | 454.819 | -11295.429865 |
| M1B | 438.231 | 469.664 | -9635.626624 |
| K14B | 439.896 | 473.676 | 1781.495436 |
| K13A | 441.992 | 480.887 | 957.446017 |
| K12 | 441.887 | 486.686 | -47.208542 |
| M2A | 441.895 | 487.180 | 8361.470340 |
| K7A | 459.050 | 474.672 | 8691.244320 |
| HZ2 | 460.205 | 476.213 | 1091.480196 |
| HZ3 | 461.342 | 477.648 | 5180.092560 |
| K8A | 471.050 | 470.440 | 3970.043160 |
| HAJ | 469.781 | 468.695 | -3742.060880 |
| HAK | 463.066 | 458.552 | -4296.173688 |
| | 倍面積 | | 1016.772430 |
| | 面積 | | 508.3862150 |
| | 地積 | | 508.38 ㎡ |
| | 坪数 | | 153.78 |

公簿　509.75


東京都豊島区池袋本町一丁目17番4号ウィン池袋101
測量業者登録番号　国土交通大臣登録第（3）27690号
株式会社　森事務所　測量士事務所
測量士代表　佐藤　将士
登録番号　第H11−769号
電話　03（3971）0003


| | |
|---|---|
| 受託番号 | No.イ4053 |
| 作成年月日 | 平成 27 年 9 月 10 日 |
| 縮尺 | 担当者　小俣巧 |
| 1／250 | |

HAK:計算点



HAJ:計算点



K8A:既設民方向金属標端

HZ3:既設民コンクリート杭

K9:新設鋲



HZ2:既設民コンクリート杭



K7A:既設民コンクリート杭端

K1B:新設民金属標

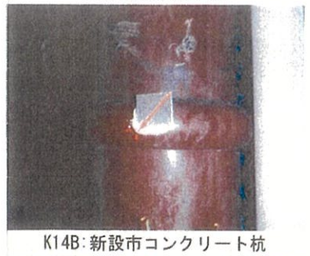

K14B:新設市コンクリート杭

K2A:新設民コンクリート杭

K13A:新設鋲

K12:新設鋲

（単位：m）

| 境界点の種類 | |
|---|---|
| コンクリート杭 | |
| 金属標 | |
| 鋲 | |
| 御影石 | |
| プラスチック杭 | |
| 計算点 | |